CHARTE GRAPHIQUE · GEOQUEST · UI 4 / 15

# PIXEL ARCADE

Insère une pièce. Pars en quête.

01 – EMBLÈME

## UN BLOC, UNE ÉTOILE

### RÈGLES D'USAGE

Un bloc rouge en relief (lumière en haut à gauche, ombre en bas à droite) avec une étoile qui sautille : touche-le pour ouvrir le menu.

**Rôle :** c'est le bouton menu, en bas au centre de l'écran. Il ouvre Profil et Catalogue.

**Taille :** 68 à 72 px dans le jeu, jamais sous 44 px (zone tactile minimale).

**Zone de protection :** 18 px au-dessus de la zone sûre de l'écran, rien d'autre à moins de 16 px. Il disparaît quand une fiche de lieu est ouverte.

### VARIANTES DES LIEUX SUR LA CARTE

Statue

Monument

Lieu de culte

Site historique

Musée

À portée

Découvert

02 – COULEURS

## HUIT BITS, CINQ COULEURS

**NUIT 8-BIT**
#1A1C2C
Contours, texte, ombres

**ÉCRAN**
#F4F4F4
Panneaux

**PIÈCE**
#FFCD75
Score, tirage payant

**HERBE**
#38B764
Carte, action principale

**CŒUR**
#B13E53
Lieux, bouton menu

### COULEURS DE JEU

Joueur
#41A6F6

Lieu à découvrir
#B13E53

Lieu découvert
#FFCD75

Prune
#5D275D

### RÉPARTITION

50 % herbe (la carte), 25 % écran, 15 % nuit, 10 % pièce. Aucun arrondi, aucun dégradé : contour de 3 px et ombre portée pleine de 4 px.

### RARETÉS DES CARTES

**Commune**
★★★★★
#94B0C2 · points ×1

**Peu commune**
★★★★★
#38B764 · points ×1.5

**Rare**
★★★★★
#3B5DC9 · points ×2.5

**Épique**
★★★★★
#B13EB1 · points ×4

**Légendaire**
★★★★★
#EF7D57 · points ×8

03 – TYPOGRAPHIE

## PRESS START CRIE, VT323 LIT

Aa

**PRESS START 2P**

Score, titres, boutons. Toujours petit (10 à 22 px) : la police est très large.

Aa

**VT323**

Tout le texte courant, de 16 à 20 px, pour rester lisible.

SCORE · PRESS START 2P 34

340 points

TITRE · PRESS START 2P 22

Cathédrale Notre-Dame de Paris

BOUTON · PRESS START 2P 16

Tirer une carte · gratuit ✦

TEXTE · VT323 14

Ton tirage gratuit du jour pour ce lieu

LÉGENDE · VT323 12

Il te manque 320 pas : marche encore un peu !

04 – INTERFACE

## LES ÉCRANS, PIÈCE PAR PIÈCE

HUD

**340** points
3 découverts sur 15 autour

4 380
pas aujourd'hui
2 430 à dépenser

+ ↻

Parvis Notre-Dame, Paris

Point zéro des routes de France est à portée : touche son pin pour tirer une carte !

JOUEUR ET LIEUX



À découvrir · à portée (halo, moins de 40 m) · découvert · sélectionné (×1,3)

FICHE DU LIEU · BOUTONS DE TIRAGE

Monument · 19 m · 50 pts

**Point zéro des routes de France**

Tirer une carte · gratuit ✦

Retirer · 1 000

Ma carte

Approche-toi encore de 25 m

Wikipédia ↗

OpenStreetMap ↗

MENU · NOTIFICATION

Profil

Catalogue

**France**
Nouveau pays débloqué dans le catalogue

CARTES À COLLECTIONNER · FACE ET DOS

Épique
★★★★★
140 pts



**Sainte-Chapelle**

Lieu de culte · Paris, France

| | |
|---|---|
| Création | 1248 |
| Patrimoine | Site protégé |

Chapelle palatine bâtie sur l'île de la Cité à la demande de Saint Louis pour abriter les reliques de la Passion, consacrée en 1248. Ses verrières du XIIIe siècle couvrent plus de 600 m².

Source : Wikipédia 29/10/2026



Le cadre prend la couleur de la rareté, l'en-tête sa teinte. Les cartes Épique et Légendaire ont un reflet qui passe en boucle.

05 – MOUVEMENT

## CE QUI BOUGE, ET COMMENT

**01**
Héros qui sautille en 2 images

**02**
Toutes les animations en steps() : pas de fluidité

**03**
Bouton gratuit qui clignote, carte qui tremble

Données © OpenStreetMap · GeoNames · OpenFreeMap